BAB II

PEMODELAN TAPAK SEDERHANA

Pemodelan tapak merupakan tahap awal dalam proses perancangan arsitektur yang bertujuan untuk merepresentasikan kondisi lahan secara visual dalam bentuk tiga dimensi. Pada tahap ini, pengguna akan membuat model dasar tapak yang mencakup batas lahan, elemen lingkungan, serta konteks sekitar sebagai dasar dalam pengembangan desain bangunan.

MEMBUAT TAPAK

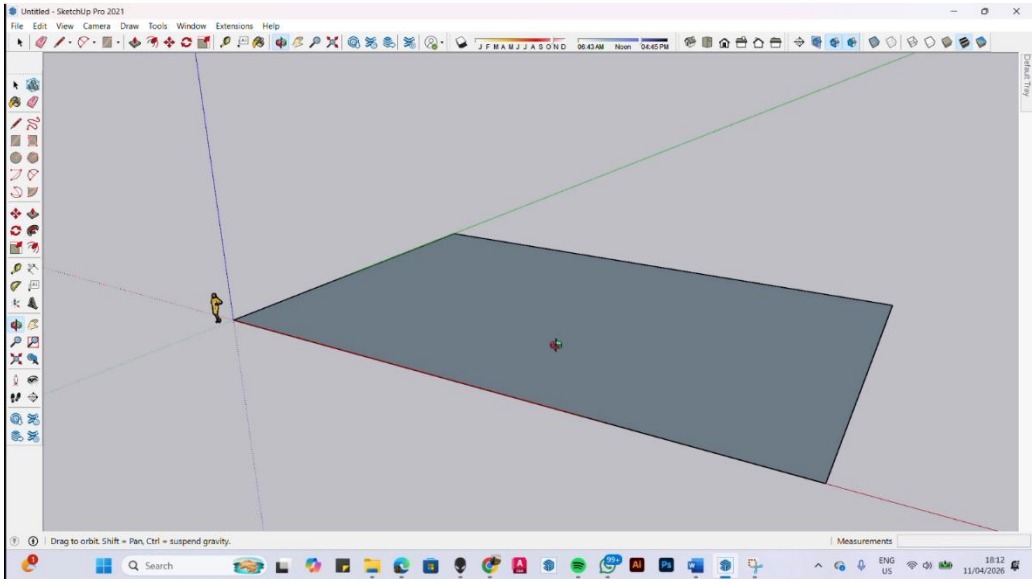

- Buatlah persegi dengan ukuran 30.00 X 20.00 dengan cara klik ikon persegi (rectangle)
- Klik di titik origin sambil menarik mouse
- Perhatikan kotak measurements sewaktu membuat persegi otomatis ditunjukkan dimensi panjang x lebar Ketik 30;20 untuk panjang 30 m dan lebar 20 m
- Klik ikon push/pull kemudian arahkan pada bidang, klik dan tarik ke atas bidang yang diberi ketinggian akan berubah warna menjadi putih/abu-abu muda. Hasilnya sebagai berikut:

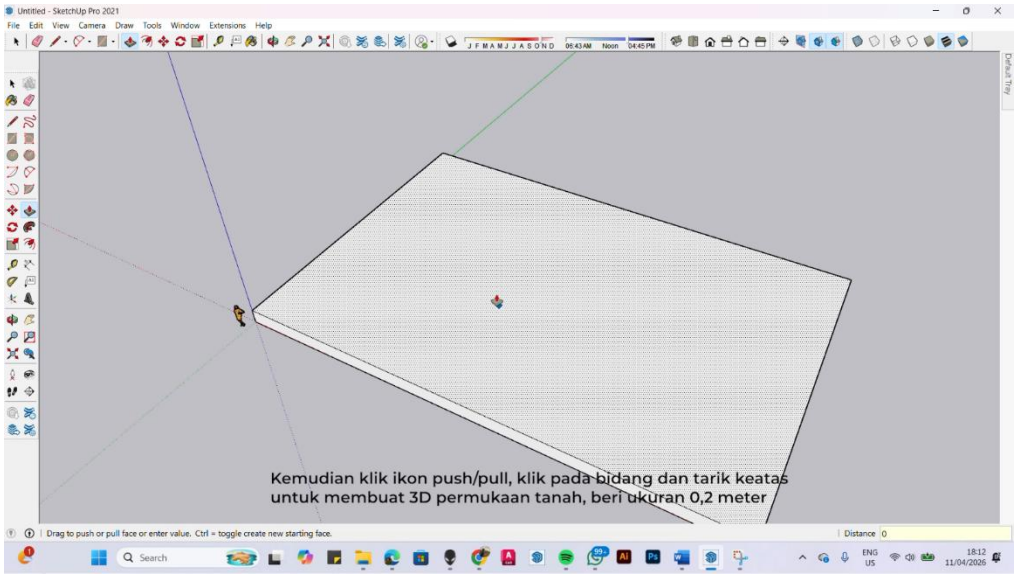

- Langkah terakhir adalah mengunci bangunan 3D, karena obyek yang kita gambar akan terhubung oleh setiap geometri yang bersentuhan dengannya di sketchup disebut "sticky"
- Pilih/seleksi kesemua bidang lantai dengan cara klik ikon seleksi (select), kemudian double klik pada bidang tersebut sehingga objek akan terseleksi semua
- Setelah terseleksi kemudian klik kanan dan pilih make group

MEMBUAT JALAN

- Buatlah persegi dengan ukuran 4.00 X 20.00 dengan cara klik ikon persegi (rectangle)
- Klik ikon rectangle pada tengah garis titik bewarna cyan perhatikan kotak measrument ketik ukuran 4;20 m

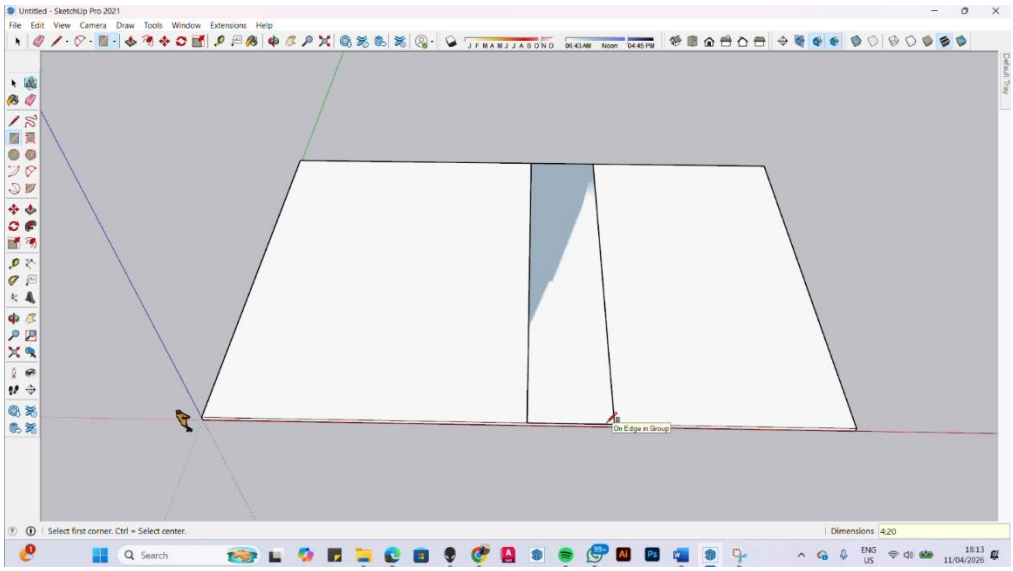

- Klik ikon push/pull kemudian arahkan pada bidang, klik dan tarik ke atas bidang yang diberi ketinggian akan berubah warna menjadi putih/abu-abu muda. Hasilnya sebagai berikut:

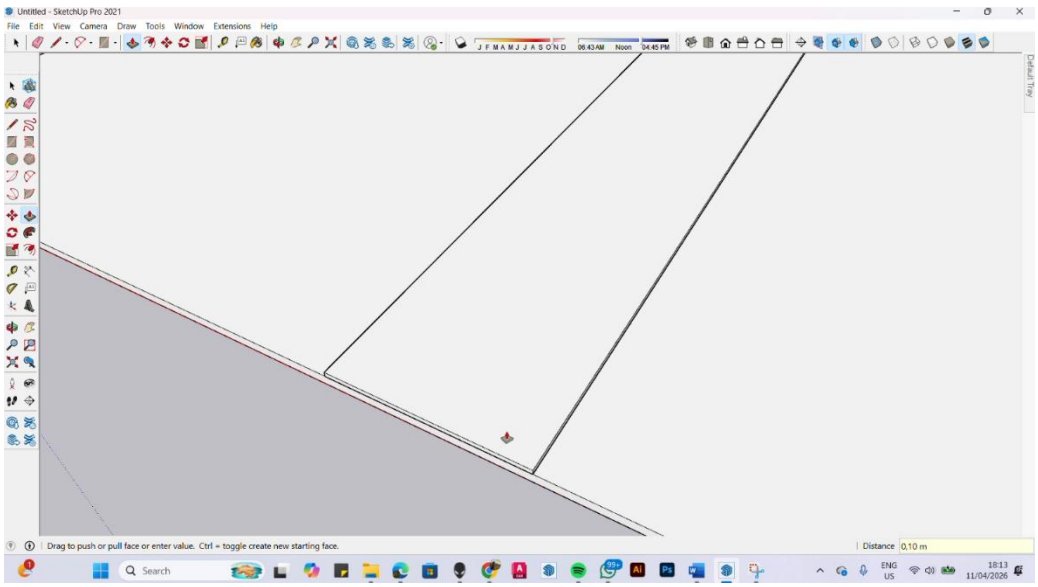

- Seleksi semua objek jalan dengan double klik sehingg objek terseleksi semua
- setelah semua terseleksi klik kanan dan pilih make group

MENAMBAHKAN VEGETASI

Pada sketchup sudah disediakan fitur 3D warehouse sebagai tempat perpustakaan model 3D daring terbesar di dunia yang dibuat khusus untuk pengguna SketchUp. Platform ini berfungsi sebagai pusat komunitas di mana desainer dapat mengunduh model siap pakai.

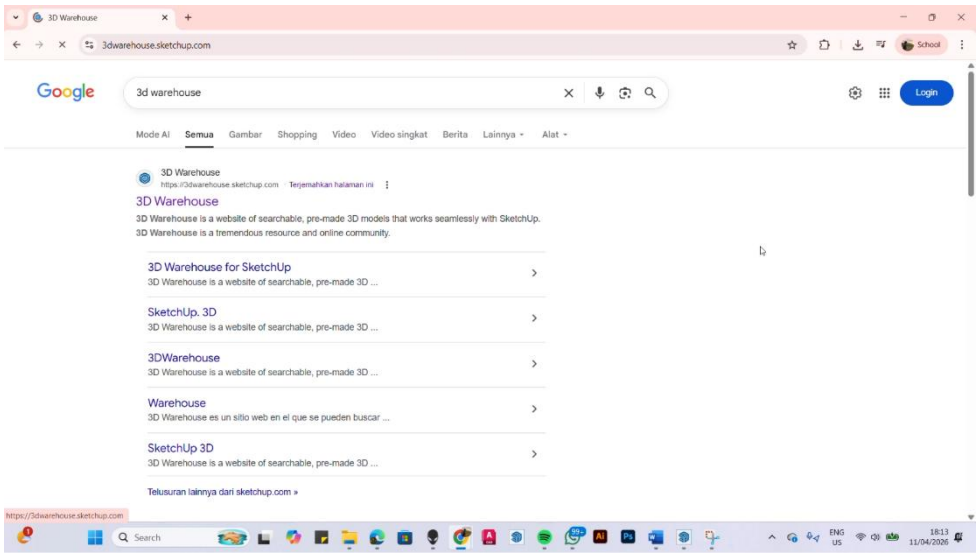

- Buka chrome anda dan tulis pada pencaharian 3D warehouse
- Buka web tersebut dan ketik pada pencahariannya menggunakan bahasa inggris, ketik "tree" dan pilih berbagai model pohon yang tersedia

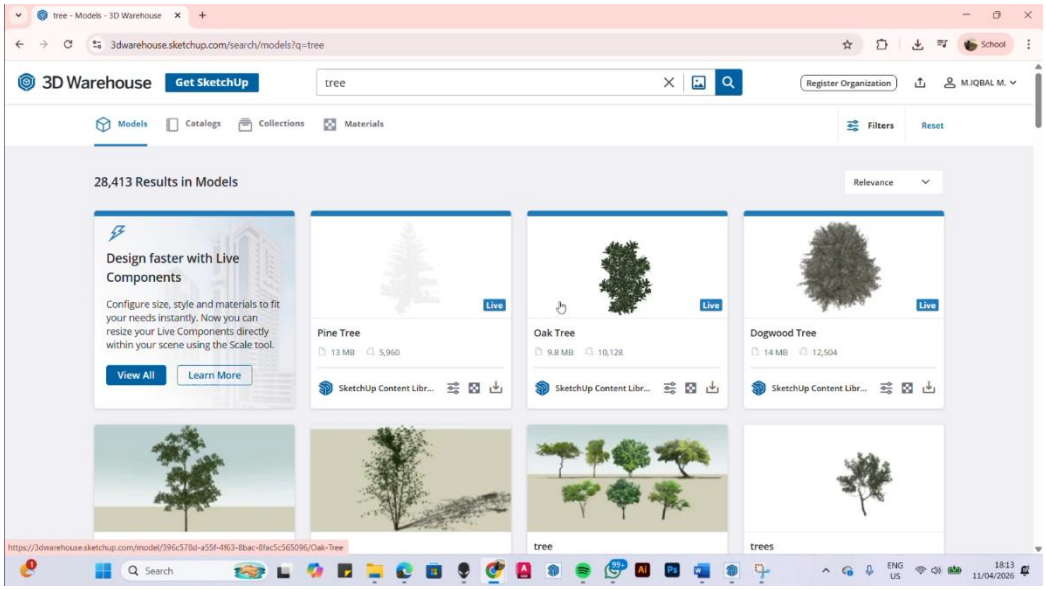

- Download model yang anda inginkan
- Setelah itu kembali ke sketchup pilih menu file klik import untuk memasukkan file model yang sudah anda download

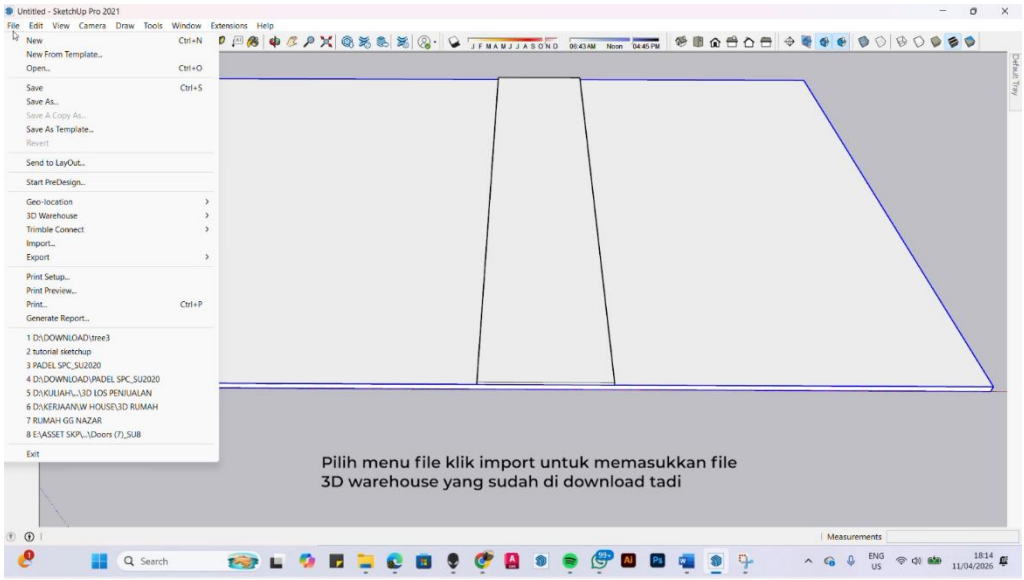

- Letakkan model pohon pada tapak yang sudah dibuat, atur letak model

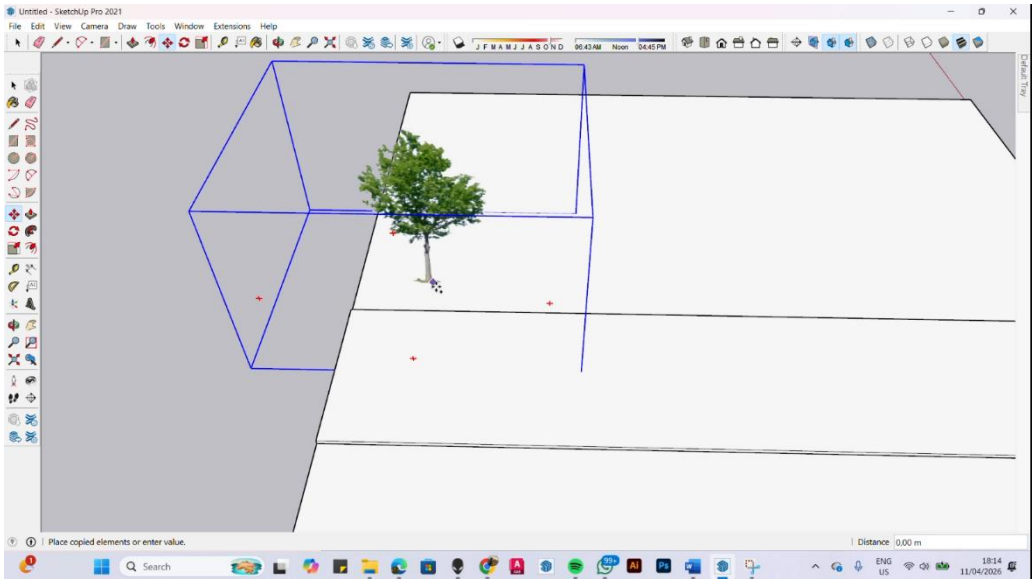

- Kemudian klik ikon move dan tekan tombol CTRL untuk copy model pohon, copy dengan jarak 3 meter sampai ke ujung tapak

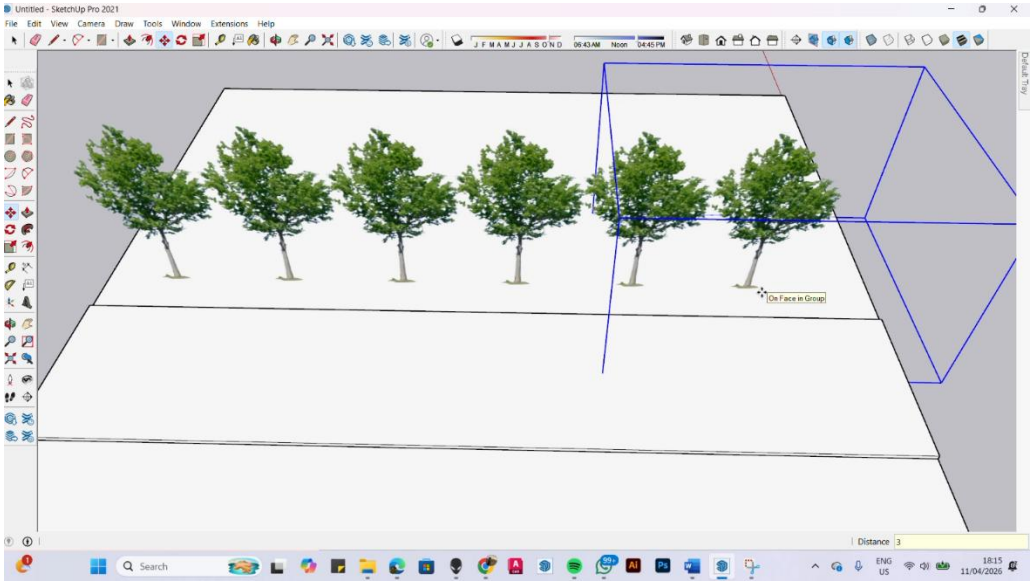

- Kemudian seleksi semua model pohon dan klik kanan make group agar model tidak berpindah dan bergabung dengan model lain

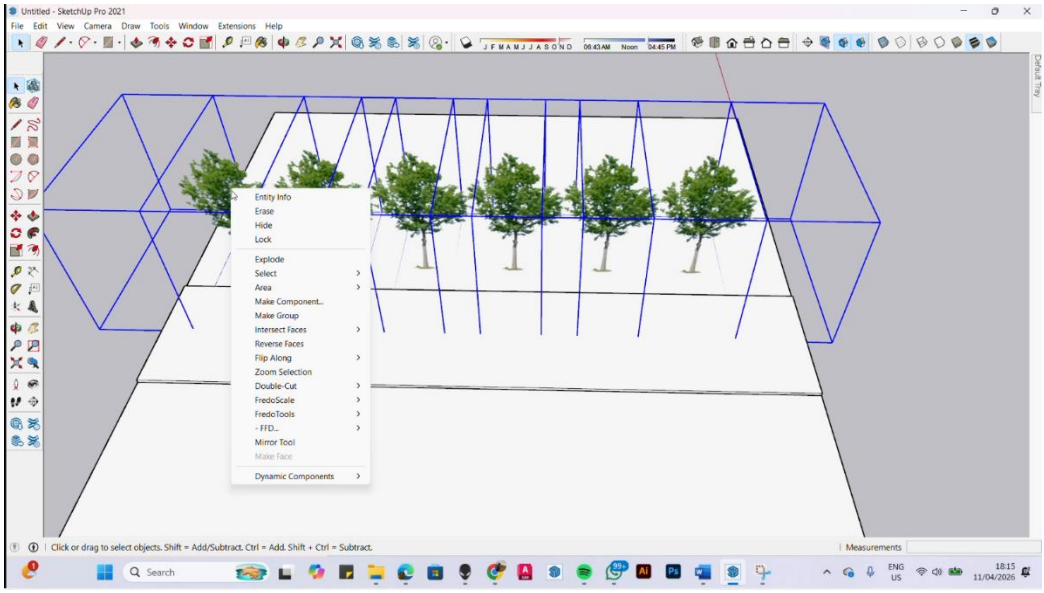

MEMBUAT BANGUNAN EKSISTING

- Buat garis bantu untuk GSB (Garis Sempadan Bangunan) dengan jarak 3 meter dari jalan

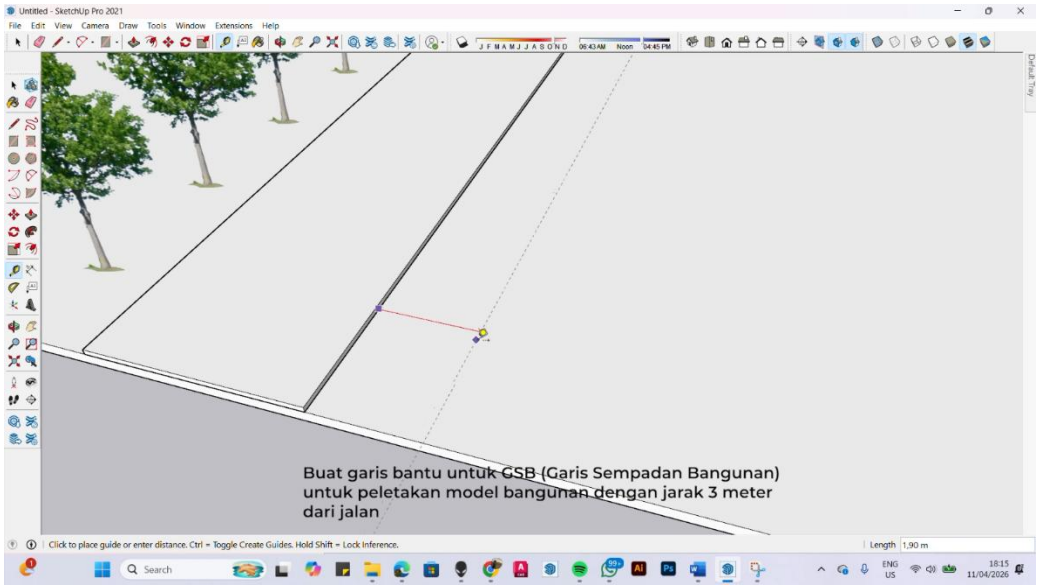

- Klik ikon rectangle untuk membuat model bangunan sederhana dengan ukuran 3;3 meter
- Kemudian klik ikon push/pull untuk membuat 3D bangunan dengan level ketinggian 3 meter

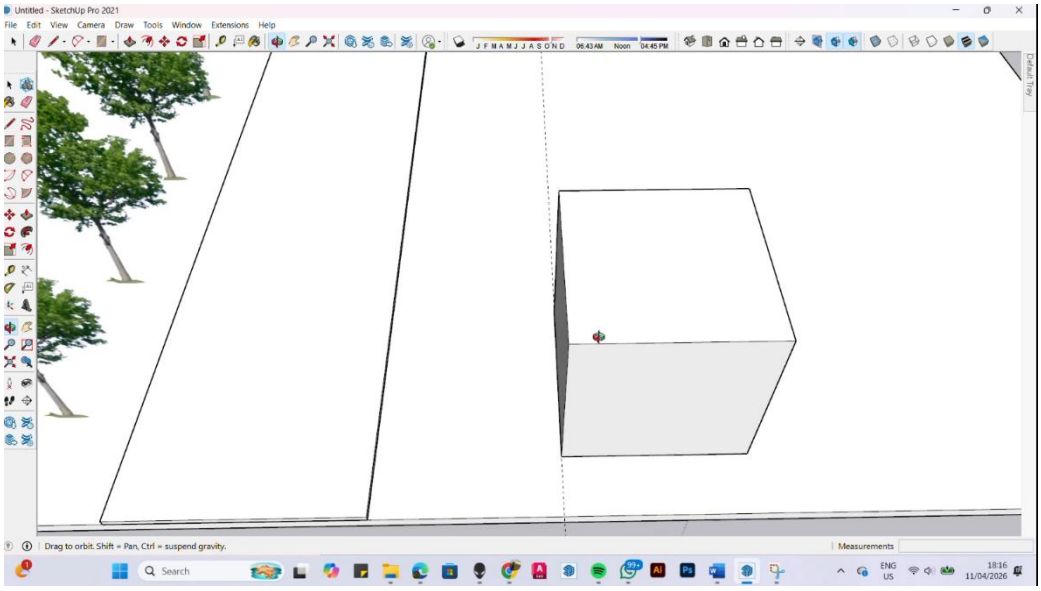

- Seleksi semua objek bangunan dengan double klik dan klik kanan dan make group

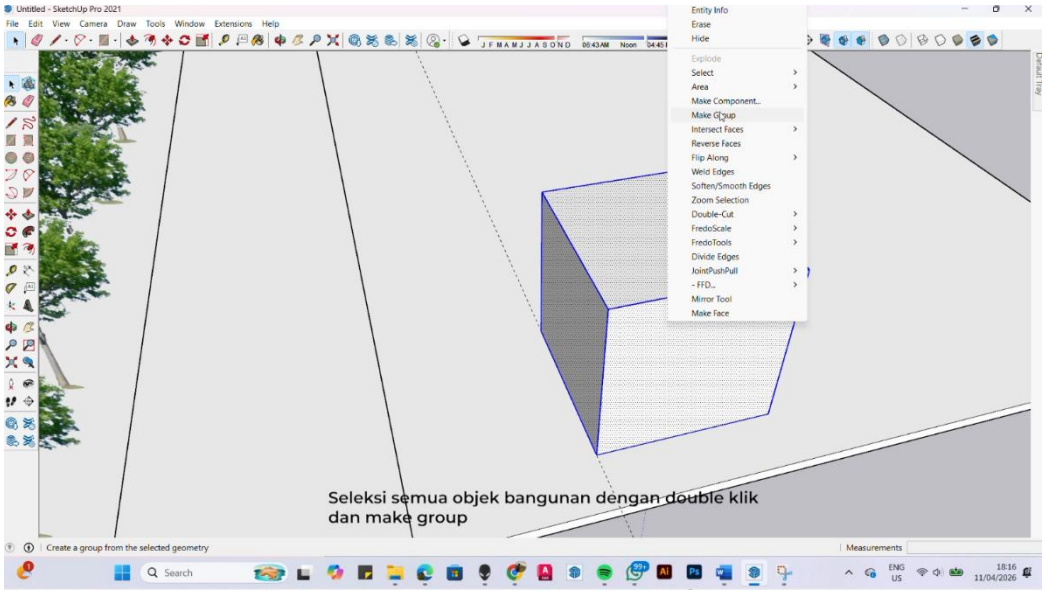

- Klik ikon move untuk copy bangunan, klik dan tekan tombol CTRL, copy bangunan dengan jarak 5 meter setiap model sampai ujung tapak

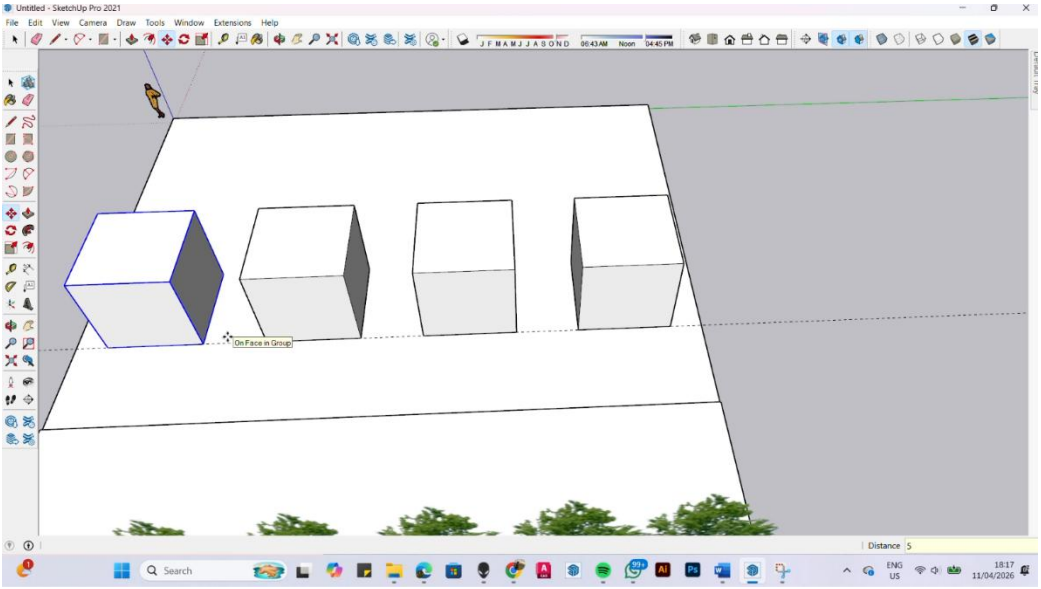

- Hapus garis bantu dengan cara klik garis tersebut dan tekan delete atau ikon erase

MEMBERI MATERIAL

Untuk memberikan pilihan material yang banyak, sketchup telah menyediakan tambahan pilihan material pada menu default tray.

- Double klik group jalan dan klik menu default tray pilih menu material pilih aspalt dan klik pada bagian bidang jalan

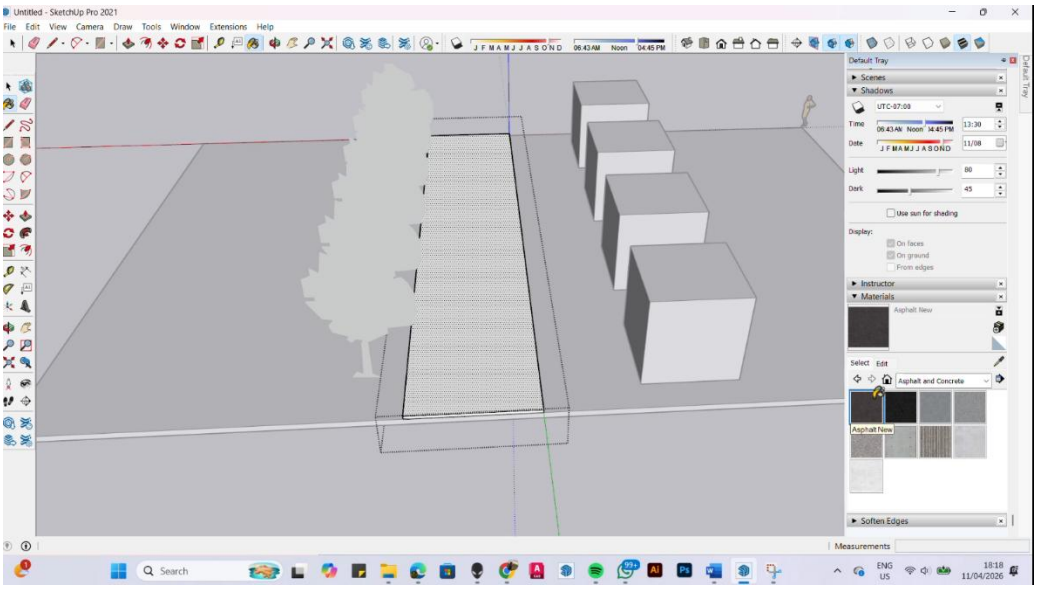

- Kemudian double klik group tapak untuk memberi material klik default tray pilih menu material pilih landscaping

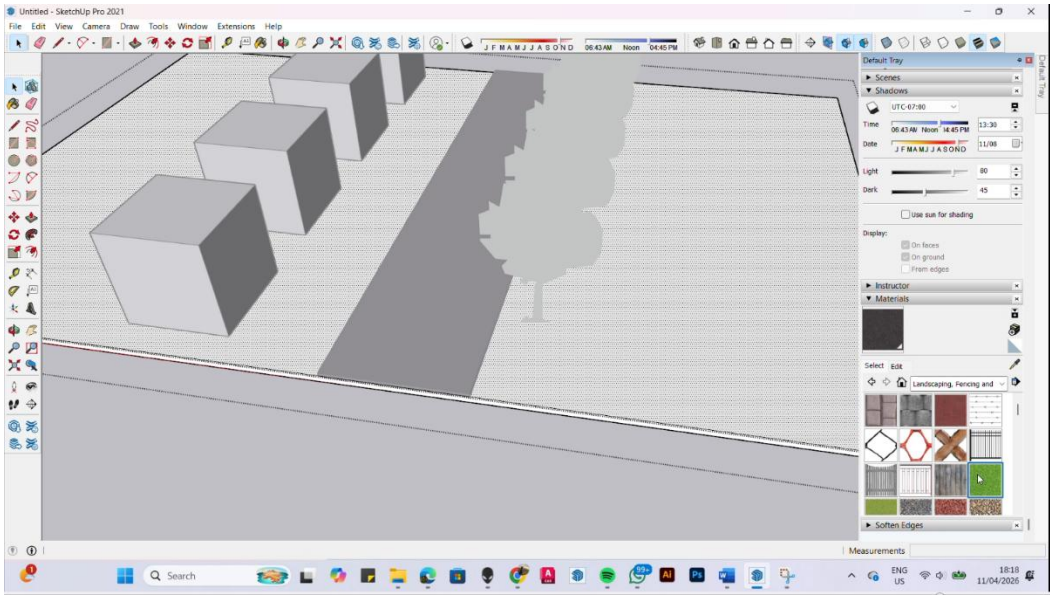
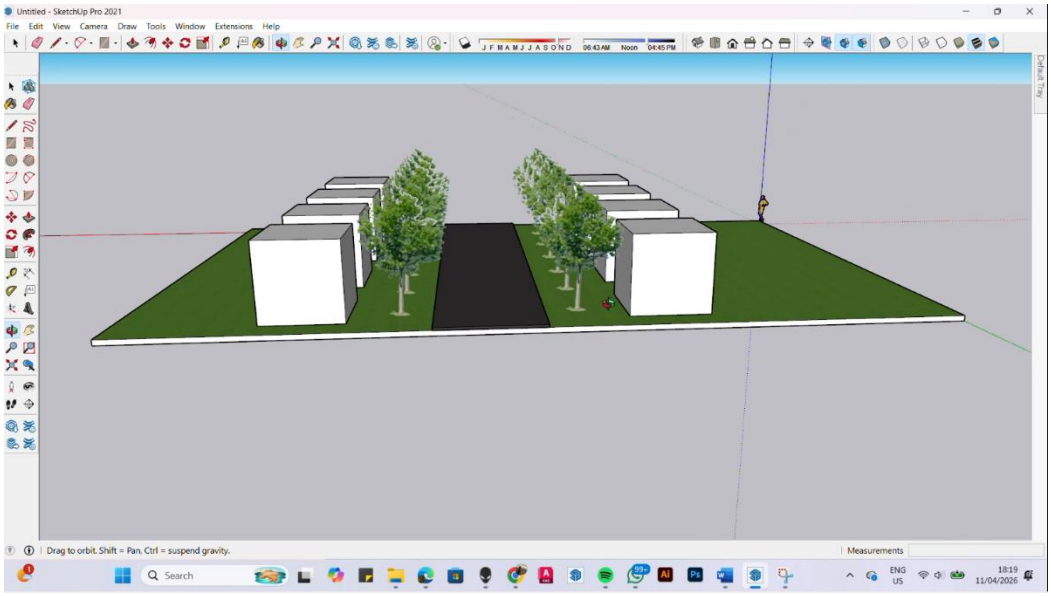
- Klik ikon move, klik group pohon tekan tombol CTRL untuk copy pohon ke jalan di bangunan
- Kemudian seleksi group bangunan, klik ikon move tekan tombol CTRL untuk copy bangunan ke belakang pohon